Étude des profils économiques et des disparités territoriales en Région Centre-Val de Loire

Ariane Dohou

ISC Paris

TABLE DES MATIERES

I. Résumé de l'étude ---------- 0

II. Introduction ---------- 0

1. Contexte et objectifs de l'étude ---------- 0

a. Contexte de l'étude ---------- 0

b. Objectifs de l'Étude ---------- 1

2. Problématique et Questions de Recherche ---------- 1

3. Démarche Analytique et Sources de Données ---------- 2

a. Sources des données utilisées ---------- 3

b. Les Étapes de l'Analyse ---------- 4

III. Audit, Nettoyage et Normalisation des Données ---------- 5

1. Traitement de la base URSSAF ---------- 5

2. Traitement de la base Sirene ---------- 5

3. Construction de la Base d'Analyse Agrégée ---------- 6

IV. Analyse des données et interprétation des résultats ---------- 7

1. Portrait Économique Global de la Région ---------- 7

a. Les Indicateurs Clés Régionaux ---------- 7

b. La Structure Sectorielle Régionale ---------- 8

2. Analyse Comparative des Départements du centre val de Loire ---------- 12

a. Les Deux Pôles de Services : Le Loiret (45) et l'Indre-et-Loire (37) ---------- 12

b. Le Cœur Industriel de la Région : Eure-et-Loir (28), Loir-et-Cher (41), Cher (18) et Indre (36) 13

c. Analyse des Secteurs en Retrait ---------- 13

3. Les Typologies d'EPCI : Une Vision Opérationnelle pour l'Action ---------- 13

a. Méthodologie du Clustering de Profils ---------- 14

b. Création de l'ADN Économique de chaque EPCI ---------- 14

c. Regroupement par l'Algorithme K-Means (avec k=4) ---------- 15

4. Cartographie des 4 Familles de Territoires ---------- 15

5. Description Détaillée des 4 Profils d'EPCI ---------- 17

a. Profil A : Le Socle de l'Économie Présentielle et Rurale (Cluster 0) ---------- 17

b. Profil B : Les Pôles Urbains, Commerciaux et de Services (Cluster 2) ---------- 18

c. Profil C : Le Cas Spécifique de "l'Interco Normandie Sud Eure" (Cluster 1) ---------- 19

d. Profil D : Le Cas Spécifique de "Les Bertranges" (Cluster 3) ---------- 19
V. Préconisations : Pour des Stratégies Territorialisées ---------- 21
1. Plan d'Action pour le Profil A : Animer le "Socle Rural et de Proximité" ---------- 21
2. Plan d'Action pour le Profil B : Renforcer les "Pôles Urbains et de Services" ---------- 22
VI. Limites de l'étude ---------- 23
VII. Gouvernance et Évolution : Vers un Observatoire Dynamique des Territoires ---------- 24
1. Instaurer un Cycle de Mise à Jour Annuel ---------- 24
2. Mettre en Place un Processus de Validation et de Recalibrage du Modèle ---------- 25
3. Instituer une Veille Stratégique et Qualitative ---------- 25
VIII. Conclusion Générale ---------- 26
IX. Annexes ---------- 27

I. RESUME DE L'ETUDE

Pour orienter sa stratégie de développement dans un contexte de profondes mutations, la Région Centre-Val de Loire a initié une analyse détaillée de son tissu économique, visant à dépasser les lectures administratives traditionnelles pour révéler ses dynamiques fonctionnelles.

En s'appuyant sur la fusion des données exhaustives de l'INSEE (Sirene) et de l'URSSAF (emploi et salaires), et en se concentrant sur les secteurs de l'industrie, du commerce et des services (hors agriculture primaire), cette étude a permis de construire un outil objectif d'aide à la décision pour des politiques publiques plus ciblées.

L'économie régionale, forte de plus de 73 000 établissements employeurs et 667 000 salariés, révèle un double visage. D'une part, un pilier industriel puissant qui, avec seulement 8,2% des entreprises, fournit 21,9% des emplois salariés, témoignant de l'importance structurelle d'établissements de grande taille.

D'autre part, un tissu économique de proximité extrêmement dense, où les services et le commerce constituent près de 70% de l'ensemble des acteurs, formant le cœur de la vitalité locale. Cette dualité se retrouve dans la hiérarchie départementale. Le Loiret et l'Indre-et-Loire s'imposent comme les deux pôles métropolitains, tirés par une économie de services diversifiés et à plus forte valeur ajoutée.

Les quatre autres départements forment une vaste ceinture où l'Industrie est le principal moteur, mais avec des profils variés, allant de la niche à haute technicité du Cher à l'économie plus localisée de l'Indre. Cependant, l'analyse la plus opérationnelle émerge du clustering des intercommunalités (EPCI), qui identifie deux grandes familles de territoires.

Le premier profil, le **"Socle Rural et de Proximité"**, regroupe 55 EPCI et constitue la base économique de la majorité du territoire, structurée autour du commerce, de la construction et des services locaux. Le second profil, les **"Pôles Urbains et de Services"**, rassemble les 25 principales agglomérations et métropoles, qui agissent comme les moteurs de la croissance régionale en concentrant l'emploi qualifié, l'innovation et les services supérieurs.

Cette nouvelle grille de lecture impose une différenciation des stratégies publiques. Pour les territoires du socle rural, la priorité doit être de **soutenir et d'animer** le tissu de TPE existant pour garantir la vitalité locale. Pour les pôles urbains, l'enjeu est de **renforcer leur compétitivité et leur attractivité** pour les talents et les filières d'avenir. En conclusion, l'étude démontre que c'est par une connaissance fine de ses territoires et par l'adaptation de son action à leurs profils distincts que la Région Centre-Val de Loire pourra piloter un développement équilibré et maximiser l'impact de ses investissement.

II. INTRODUCTION

1. Contexte et objectifs de l'étude

a. Contexte de l'étude

Le paysage économique contemporain est marqué par des mutations profondes et rapides qui imposent aux territoires de repenser leurs stratégies de développement. La double transition numérique et écologique, l'évolution des chaînes de valeur mondiales et les nouvelles exigences en matière de résilience économique obligent les acteurs publics à faire preuve d'une agilité et d'une vision renouvelées. Dans ce cadre, la Région Centre-Val de Loire, forte de sa position géographique stratégique et de son tissu économique diversifié, se trouve à un carrefour décisif.

Historiquement ancrée dans une tradition industrielle puissante, notamment dans les secteurs de la cosmétique, de la pharmacie et de la sous-traitance de pointe, la région est également un pôle logistique majeur et un territoire au patrimoine culturel et naturel de premier plan. Cependant, cette richesse recouvre des réalités territoriales hétérogènes, avec des bassins d'emploi aux dynamiques contrastées, et des défis communs liés à la modernisation de l'appareil productif et à l'attraction des talents.

Conscient de cette complexité, le Conseil Régional a engagé une démarche visant à faire évoluer ses politiques d'intervention. L'ambition est de passer d'un soutien économique global à une stratégie d'investissement proactive, ciblée et différenciée, capable de répondre avec pertinence aux enjeux spécifiques de chaque territoire. Cette étude s'inscrit au cœur de cette ambition, en mobilisant l'analyse de données massives pour fournir un diagnostic objectif et approfondi, destiné à éclairer la prise de décision et à optimiser l'allocation des ressources publiques.

Le périmètre de cette analyse a été volontairement concentré sur les secteurs de l'industrie, de la construction, du commerce et des services. Le secteur agricole primaire a été exclu du champ quantitatif de l'étude en raison de l'absence de données sur l'emploi salarié régional de ce secteur.

b. Objectifs de l'Étude

Pour répondre à ce besoin de pilotage stratégique, l'étude poursuit un objectif général qui se décline en plusieurs objectifs spécifiques et opérationnels.

❖ **Objectif Général**

L'objectif général de cette étude est de fournir au Conseil Régional **une analyse approfondie et multi-scalaire du tissu économique afin de construire un outil d'aide à la décision pour des politiques de développement territorialisées, efficaces et pertinentes.**

❖ **Objectifs Spécifiques**

Plus spécifiquement, il s'agira de :

- **Dresser un portrait quantitatif de l'économie régionale ;**
- **Mener une analyse comparative des six départements ;**
- **Identifier des typologies de territoires opérationnels à l'échelle des EPCI** (intercommunalités) ;
- **Et formuler des préconisations stratégiques différenciées**.

2. Problématique et Questions de Recherche

Le défi pour la Région Centre-Val de Loire n'est pas une absence de volonté politique ou de données, mais plutôt la complexité inhérente à son tissu économique. Face à une mosaïque de territoires aux dynamiques hétérogènes, une stratégie "taille unique" s'avère inefficace. Pour allouer les ressources publiques de manière judicieuse et maximiser l'impact des politiques de développement, une compréhension fine des réalités économiques locales est un prérequis indispensable. Le passage d'une observation statistique à une véritable intelligence territoriale constitue donc l'enjeu central de cette étude.

Ainsi il parait indispensable de se demander : **Comment l'analyse de données massives permet-elle de révéler la véritable géographie économique de la Région Centre-Val de Loire ?**

Pour répondre à cette problématique d'ensemble, notre travail d'investigation s'est structuré autour de quatre questions spécifiques, correspondant aux étapes clés de notre analyse :

- Quel est le poids économique réel de la région et quels sont les secteurs qui constituent véritablement les piliers de son économie en termes d'emploi, de richesse distribuée et de densité d'entreprises ?
- Les six départements de la région présentent-ils des profils économiques homogènes, ou observe-t-on au contraire des spécialisations, des forces et des vulnérabilités qui leur sont propres ?
- Est-il possible de regrouper les intercommunalités (EPCI) en un nombre restreint de "profils-types" partageant un ADN économique similaire ?
- Quelles actions ciblées peuvent être proposées pour chaque typologie de territoire afin de répondre à ses enjeux spécifiques et d'optimiser l'impact des politiques régionales ?

Le présent rapport s'attache à répondre de manière détaillée et argumentée à chacune de ces questions, afin de fournir à la Région les clés d'une stratégie de développement économique fondée sur une connaissance objective et approfondie de ses territoires.

3. Démarche Analytique et Sources de Données

La présente étude a été menée dans le strict respect du Règlement Général sur la Protection des Données (RGPD). L'analyse repose sur des données d'entreprises (personnes morales) et des données statistiques déjà agrégées, garantissant l'anonymat. Une déclaration de conformité détaillée, précisant la nature des données et les méthodes de traitement, est disponible en **Annexe A** de ce rapport.

Pour répondre aux questions de recherche définies précédemment, une démarche analytique quantitative et multi-scalaire a été mise en œuvre. Cette approche a pour objectif de transformer des données administratives brutes en une intelligence territoriale directement exploitable pour la prise de décision stratégique. La méthodologie repose sur deux piliers : la fusion de sources de données publiques de référence et un processus d'analyse structuré en plusieurs étapes successives, allant du diagnostic global à la modélisation de typologies de territoires.

a. Sources des données utilisées

La robustesse de l'étude est assurée par le croisement de plusieurs jeux de données officiels qui, une fois combinés, offrent une vision à 360° du tissu économique. Le périmètre de l'analyse a été délimité pour se concentrer sur les secteurs de l'industrie, de la construction, du commerce et des services, en excluant le secteur de l'agriculture en raison de l'absence de données récents sur ce secteur.

- **La Base de Données Sirene (INSEE) :** Elle a servi de fondation structurelle à notre analyse, fournissant un recensement exhaustif des établissements actifs en région Centre Val de Loire. On y retrouve plus d'une centaine de variables, mais seulement quelques-unes ont été utilisés dans notre étude. Il s'agit

  - du **SIRET** pour le décompte des établissements,
  - des éléments de localisations comme le **nom du département**, **Code EPCI de l'établissement** pour structurer l'analyse territoriale
  - le **secteur d'activité de l'entreprise** (Industrie, commerce, construction, intérim, Autres services marchands hors intérim, services non marchand et Hôtellerie-restauration) pour la qualification économique,
  - et **la Tranche d'effectif comme indicateur de la taille des entreprises**.

- **Les Données sur l'Emploi Salarié (URSSAF) :** Cette source a fourni la mesure du poids économique et social des activités. Elle a permis de quantifier l'impact réel des secteurs en termes d'emploi et de richesse distribuée. Les variables utilisées dans cette base sont : les **effectifs salariés (brut)** et la **masse salariale (brut)**. Elles sont agrégées par département et par grand secteur d'activité afin d'évaluer la contribution de chaque segment de l'économie.
- **Les Référentiels Géographiques et de Nomenclature (INSEE / IGN) :** un fond de carte des EPCI (format GeoJSON) a été utilisé pour la visualisation cartographique des résultats du clustering.

b. Les Étapes de l'Analyse

Afin de répondre à notre problématique, nous avons mis en place un plan d'analyse en 4 étapes :

- **Étape 1 : Ingénierie des Données et Construction de la Base d'Analyse** Cette phase préparatoire, essentielle à la qualité des résultats, a consisté à nettoyer, filtrer (pour ne retenir que les entreprises actives de la région hors secteur agricole) et harmoniser les différentes sources. Le principal travail a été de fusionner les données structurelles de Sirene avec les données économiques de l'URSSAF pour créer une base de données agrégée unique, au niveau du croisement Département / Secteur.
- **Étape 2 : Analyse Descriptive et Comparative**

Cette première phase d'exploitation des données a permis d'établir un diagnostic global. Nous avons d'abord calculé les indicateurs clés à l'échelle de la région pour définir un point de référence. Ensuite, nous avons mené une analyse comparative des six départements en construisant un tableau de bord synthétique, mettant en regard leur poids économique, leur structure d'emploi et leurs secteurs dominants.

- **Étape 3 : Identification des Typologies de Territoires par Clustering**

Pour dépasser l'analyse par département, jugée trop large pour une action opérationnelle, nous avons mis en œuvre une analyse de clustering à l'échelle des EPCI. A cet effet, nous avons fait :

- **Le profilage des EPCI :** Chaque intercommunalité a été caractérisée par un "profil" ou "ADN" économique, représentant la part de chaque grand secteur dans son tissu d'établissements ;
- **La modélisation K-Means :** L'algorithme K-Means a été appliqué sur ces profils pour regrouper les EPCI aux caractéristiques similaires en un nombre restreint de "familles" ou "clusters".
- **La validation Méthodologique :** Le choix de retenir 4 clusters a été objectivement validé par la "méthode du coude", qui garantit que la typologie obtenue est statistiquement robuste et non arbitraire.

- **Étape 4 : Synthèse Stratégique et Visualisation**

La dernière étape a consisté à interpréter les résultats de ces analyses pour en extraire des enseignements stratégiques. Cela inclut la description détaillée de chaque typologie d'EPCI, la création de visualisations parlantes (cartes, graphiques comparatifs) et la traduction des constats analytiques en préconisations pour guider l'action publique régionale.

III. AUDIT, NETTOYAGE ET NORMALISATION DES DONNEES

Les fichiers bruts obtenus sur les divers sites ont nécessité une série d'opérations de préparation pour garantir leur qualité, leur cohérence et leur compatibilité en vue d'une fusion fiable. Cette étape d'ingénierie des données s'est déroulée comme suit :

1. Traitement de la base URSSAF

Les données de cette base sont les plus récents : ils couvrent la période du premier trimestre de l'année 2025. L'objectif ici était d'isoler les informations essentielles à notre analyse et de les standardiser. A cet effet, nous avons procéder à :

- **La sélection des variables :** Seules les quatre colonnes nécessaires à l'analyse ont été conservées : Département, Grand secteur d'activité, Effectifs salariés (brut), et Masse salariale (brut) ;
- **La normalisation des formats :** Le type de la colonne Département a été forcé en chaîne de caractères (string) pour assurer des jointures fiables avec la base Sirene et éviter toute interprétation numérique incorrecte des codes départementaux.
- **Harmonisation :** Les colonnes ont été renommées (Departement, Secteur, Effectifs, Masse_Salariale) pour créer un standard commun aux deux jeux de données.

2. Traitement de la base Sirene

La base Sirene, plus granulaire, a fait l'objet d'un traitement plus approfondi pour définir le périmètre exact de l'analyse.

- **Contrôle de qualité :** Une vérification de l'unicité des identifiants SIRET a été menée pour s'assurer de l'absence de doublons qui auraient pu fausser les décomptes.
- **Définition du périmètre d'analyse :** Deux filtres stratégiques ont été appliqués à ce niveau de l'analyse :
  - **Exclusion du secteur agricole :** les établissements appartenant au grand secteur "Agriculture" ont été retirés de la base. En effet, les données de l'Urssaf ne prennent pas en compte le secteur agricole et les données sur le site de l'Urssaf ne sont pas à jour. Nous n'avions pas le moyen de faire le croisement entre les données sur les établissements du secteur et les données salariales. Etant donné leur faibles nombres (8% des établissements de la région), ils ont été exclus de l'étude.
  - **Focalisation sur le tissu employeur :** L'analyse a été ciblée sur les établissements ayant une activité salariale. Les entités où le Caractère employeur de l'établissement était "Non" (indépendants et auto-entrepreneurs sans salariés, sièges sociaux sans personnel propre, etc.) ont été exclues. Ce choix permet d'aligner parfaitement le décompte des établissements de la base Sirene avec les données sur l'emploi salarié de la base URSSAF.
- **Harmonisation des données :**
  - Les libellés de secteurs ont été standardisés pour garantir la cohérence (par exemple, "Hébergement-restauration" a été normalisé en "Hôtellerie-restauration" pour correspondre aux autres sources).
  - Les colonnes Département de l'établissement et Grands secteurs ont été renommées (Departement, Secteur) pour permettre la fusion.

3. Construction de la Base d'Analyse Agrégée

L'étape finale de la préparation a consisté à fusionner ces deux sources de données nettoyées.

- La base **Sirene** a d'abord été agrégée pour calculer le **nombre d'établissements employeurs** pour chaque couple Departement / Secteur.

- Cette table agrégée a ensuite été **fusionnée** avec la table préparée de l'**URSSAF** en utilisant les colonnes Departement et Secteur comme clés de jointure.

Ce processus a abouti à la création d'une **base de données finale, unique et cohérente**, contenant, pour chaque secteur dans chaque département, le nombre d'établissements employeurs, le total des effectifs salariés et la masse salariale correspondante. C'est sur ce jeu de données fiable que reposent les analyses descriptives et comparatives de notre étude.

IV. ANALYSE DES DONNEES ET INTERPRETATION DES RESULTATS

1. Portrait Économique Global de la Région

Avant d'explorer les dynamiques propres à chaque territoire, il est indispensable de faire un portrait global de l'économie de la Région Centre-Val de Loire. Cette vision d'ensemble, établie sur le périmètre de l'étude, nous fournit les ordres de grandeur et les caractéristiques structurelles qui serviront de point de référence pour toutes nos analyses comparatives ultérieures.

a. Les Indicateurs Clés Régionaux

L'analyse des données consolidées nous permet de quantifier le poids et la nature de l'économie régionale à travers quatre indicateurs fondamentaux qui se présentent comme suit :

```
================================================================================
--- ANALYSE DESCRIPTIVE DE LA RÉGION CENTRE-VAL DE LOIRE ---
================================================================================
Nombre total d'établissements       : 73 471
Nombre total d'emplois salariés     : 667 472
Masse salariale totale (trimestrielle)   : 5.3 milliards d'€
Salaire mensuel moyen régional      : 2 627 €
```

Source : Analyses de l'auteur

Ces chiffres dressent le portrait d'un écosystème économique conséquent et nous livrent un premier enseignement majeur sur sa structure.

En rapportant le nombre total de salariés au nombre d'établissements, on obtient une taille moyenne de **9,1 salariés par établissement**. Ce ratio confirme que l'économie de la Région Centre-Val de Loire repose fondamentalement sur un tissu extrêmement dense de **Très Petites Entreprises (TPE)**, dont l'effectif est par définition inférieur à 10 salariés.

Cette caractéristique suggère une économie dotée d'une grande capillarité territoriale et d'un potentiel de flexibilité, mais dont les acteurs majoritaires disposent individuellement de faibles capacités d'investissement et de projection sur les marchés extérieurs. La politique régionale doit impérativement intégrer cette réalité des TPE comme la maille de base de son économie.

La **masse salariale trimestrielle de 5,3 milliards d'euros** représente la richesse directement et régulièrement injectée dans l'économie locale. Annualisée à plus de 21 milliards d'euros, elle constitue le flux financier qui alimente la consommation des ménages et les recettes des collectivités, et mesure le poids économique réel des secteurs étudiés.

Enfin, le **salaire mensuel moyen de 2 627 €** devient notre **baromètre régional de la qualité des emplois**. Ce chiffre, bien que synthétique, servira de point de comparaison essentiel. L'enjeu des analyses qui suivront sera de décomposer cette moyenne pour identifier les départements, les territoires et les secteurs qui parviennent à générer des emplois à plus forte valeur ajoutée (et donc à plus haute rémunération) et ceux qui, au contraire, se situent en deçà de cette moyenne régionale.

Ce portrait global, celui d'une économie de TPE/PME générant plus de 20 milliards d'euros de salaires annuels, est la toile de fond sur laquelle les spécificités de chaque territoire vont maintenant pouvoir être analysées.

b. La Structure Sectorielle Régionale

L'analyse de la répartition des établissements et des salariés par grand secteur d'activité est essentielle pour comprendre les piliers sur lesquels repose l'économie du Centre-Val de Loire. L'observation croisée de ces deux répartitions, basée sur les données consolidées, révèle des profils de secteurs très distincts et complémentaires, et met en lumière le double visage de l'économie régionale.

❖ Répartition des établissements employeurs par secteur

Cette analyse nous renseigne sur la densité du tissu entrepreneurial. Elle met en évidence les secteurs où les acteurs économiques sont les plus nombreux.

La répartition est la suivante :

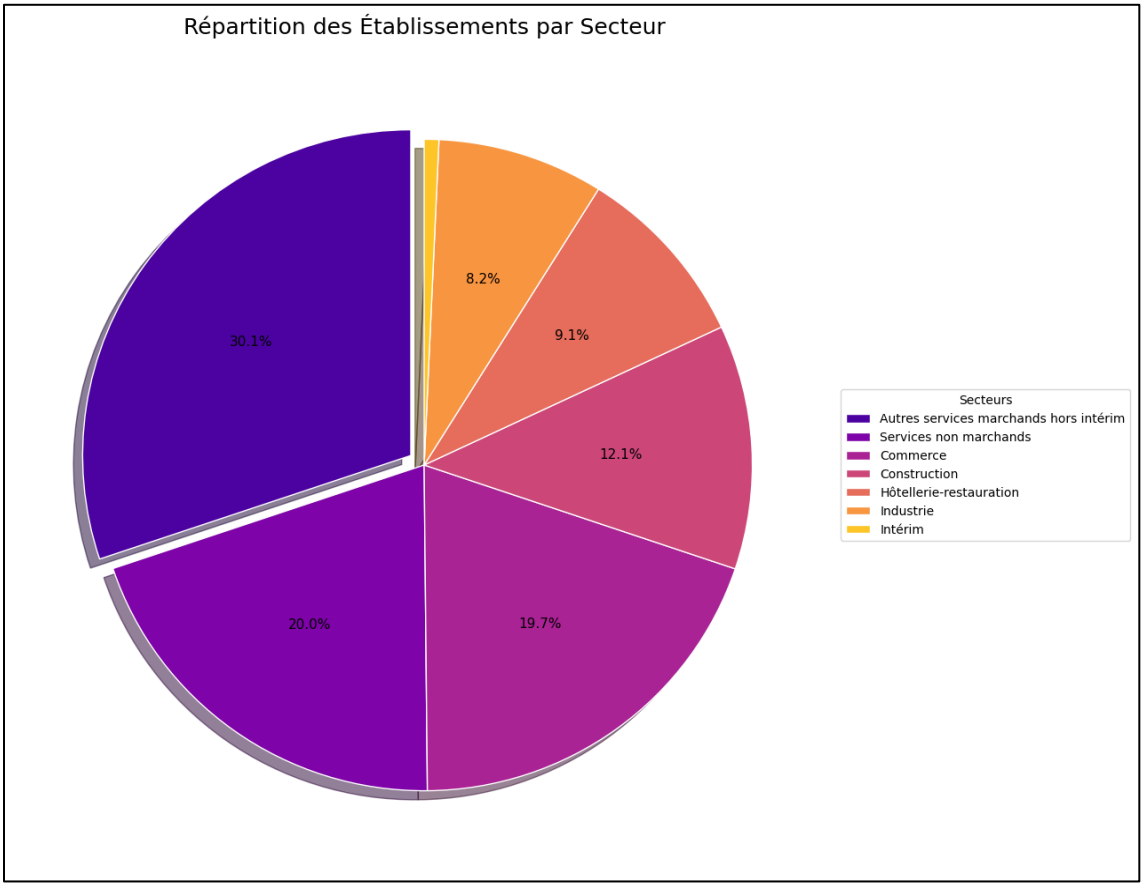

Source : Analyses de l'auteur

Le constat est clair : près de **70% des établissements employeurs** de la région (hors agriculture) appartiennent aux catégories des "Services" (marchands et non marchands) et du "Commerce". Cette structure témoigne d'une économie de proximité et de services très dense, composée d'une multitude d'acteurs de tailles variées.

- **Répartition des salariés employeurs par secteur**

La perspective change de manière significative lorsque l'on s'intéresse au volume d'emplois salariés, qui mesure le poids réel de chaque secteur dans le marché du travail régional.

La répartition des salariés est la suivante :

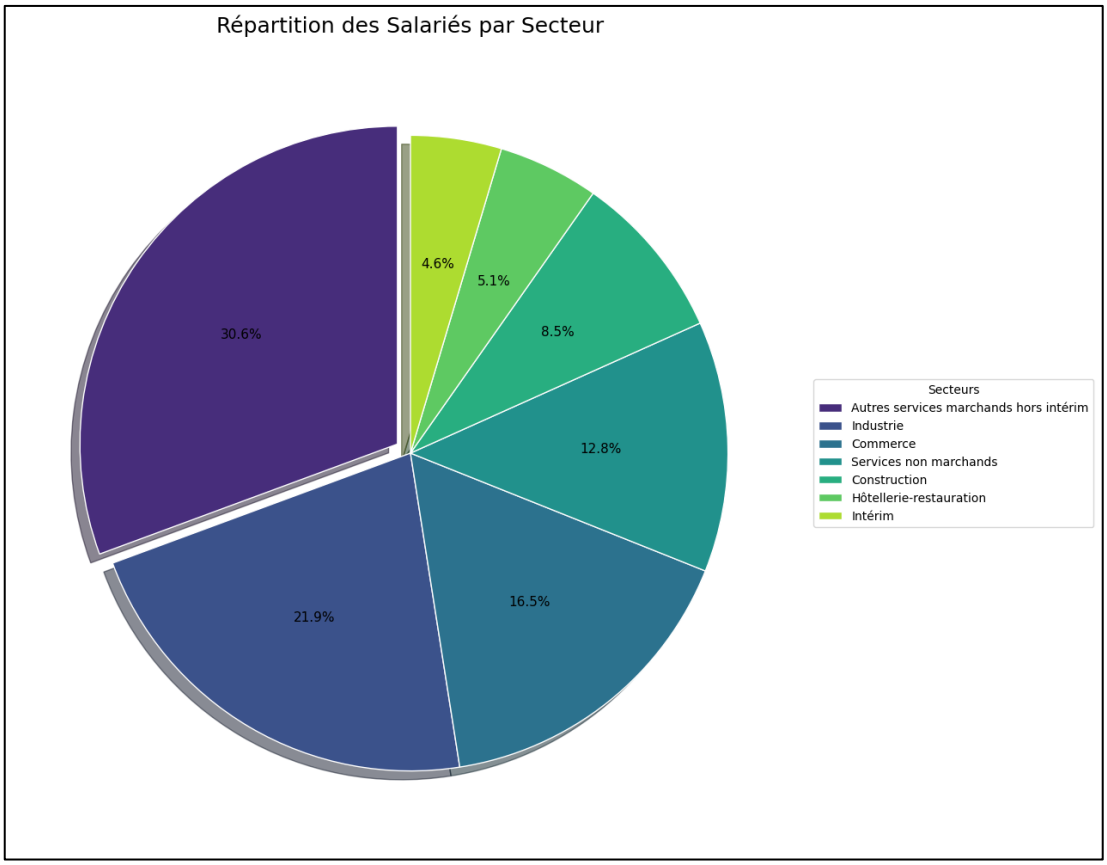

Source : Analyses de l'auteur

Ici, les "Autres services marchands" confirment leur statut de premier pôle d'emploi. Cependant, le fait le plus marquant est la deuxième place de l'Industrie, qui devance très nettement le Commerce et les Services non-marchands.

- **Analyse Croisée et Synthèse Stratégique**

La comparaison de ces deux classements révèle la véritable structure de l'économie régionale :

- **Le Profil de l'Industrie : Le Pilier de l'Emploi à Grande Échelle** L'enseignement le plus important est le profil unique du secteur industriel. Alors qu'il ne représente que **8.2%** des établissements, il concentre **21.9%** de tous les emplois salariés de la région. Cela signifie que l'industrie est structurée par des **entreprises de taille significativement plus grande** que la moyenne. Chaque établissement industriel est, en moyenne, un employeur beaucoup plus important que dans les autres secteurs. L'industrie manufacturière demeure donc un pilier fondamental de la stabilité de l'emploi régional.
- **Le Profil des Services et du Commerce : Le Tissu Dense de l'Économie** Les "Autres services marchands", le "Commerce" et les "Services non-marchands" représentent à eux trois près de **70% des établissements** mais "seulement" **59.7% des salariés**. Cela confirme leur profil de secteurs composés d'une très grande majorité de TPE et de PME, qui assurent le maillage économique et les services sur l'ensemble du territoire.

En conclusion, ce portrait sectoriel révèle une économie régionale qui s'appuie sur deux forces complémentaires :

- Une **base industrielle puissante**, qui, bien que moins dense en nombre d'entreprises, reste le grand pourvoyeur d'emplois salariés à grande échelle.
- Un **tissu économique de services et de commerce extrêmement dense**, constitué d'une myriade d'entreprises de plus petite taille, qui forme le cœur de l'économie de proximité et des services aux entreprises.

2. Analyse Comparative des Départements du centre val de Loire

Le tableau de bord (Voir annexe 1) que nous avons construit met en lumière une géographie économique régionale clairement hiérarchisée et des profils départementaux bien distincts. L'analyse croisée des indicateurs quantitatifs et des spécialisations sectorielles révèle une organisation structurée autour de deux pôles métropolitains de services et d'une vaste ceinture industrielle.

a. Les Deux Pôles de Services : Le Loiret (45) et l'Indre-et-Loire (37)

Le Loiret et l'Indre-et-Loire s'affirment comme les deux poids lourds de la région. Fait marquant, ils partagent la même spécialisation : leur secteur dominant est la catégorie des **"Autres services marchands hors intérim"**. Cela indique des économies métropolitaines diversifiées, fortement orientées vers les services aux entreprises et aux particuliers qui ne relèvent pas des catégories traditionnelles. Leurs profils se distinguent néanmoins sur la qualité et la structure de l'emploi :

- **Le Loiret (45)** est le leader économique. Avec un **salaire moyen de 2 710 €** et une **taille moyenne d'établissement de 10,2 salariés**, il présente le profil le plus robuste de la région, caractéristique d'un pôle à forte valeur ajoutée capable d'accueillir des entreprises de plus grande taille.
- **L'Indre-et-Loire (37)**, second pôle majeur, affiche des indicateurs légèrement en retrait avec un **salaire moyen de 2 652 €** et une taille moyenne de 9,6 salariés. Cela dessine le portrait d'un pôle de services également très dynamique mais dont la structure repose sur des entreprises de plus petite taille ou des sous-secteurs à plus faible niveau de rémunération.

b. Le Cœur Industriel de la Région : Eure-et-Loir (28), Loir-et-Cher (41), Cher (18) et Indre (36)

Une large "ceinture industrielle" traverse la région, puisque les quatre autres départements ont pour secteur dominant l'**Industrie**. Cela confirme le poids structurel de ce secteur en dehors des deux grandes métropoles. Cependant, derrière cette spécialisation commune se cachent des réalités différentes :

- **L'Eure-et-Loir (28)** et le **Cher (18)** se distinguent par des salaires moyens relativement élevés (respectivement **2 607 €** et **2 598 €**), suggérant la présence de filières industrielles à forte technicité et haute valeur ajoutée.
- Le **Loir-et-Cher (41)** et l'**Indre (36)** présentent les salaires moyens les plus faibles de la région (respectivement **2 535 €** et **2 448 €**). Leur base industrielle est donc vraisemblablement orientée vers des activités manufacturières plus traditionnelles ou à plus forte intensité de main-d'œuvre moins qualifiée.

c. Analyse des Secteurs en Retrait

L'analyse des secteurs les moins représentés est également instructive. Le fait que l'**Intérim** soit le secteur le moins dense (le moins d'établissements) dans tous les départements est structurel : il s'agit d'un secteur concentré avec peu d'agences physiques. Plus révélateur, le secteur le plus faible économiquement (en masse salariale) est, pour une majorité de départements, l'**Hôtellerie-restauration**. Bien que dense en établissements et essentiel à la vie locale, ce secteur génère globalement une masse salariale plus faible que les autres grands secteurs, en raison de salaires moyens souvent moins élevés et d'une plus petite taille d'entreprise.

En conclusion, cette analyse comparative présente le portrait d'une région dont l'économie est clairement polarisée : deux métropoles dominées par un secteur des services diversifié, et quatre autres départements formant un vaste territoire industriel aux profils variés.

3. Les Typologies d'EPCI : Une Vision Opérationnelle pour l'Action

Si l'analyse départementale présentée au chapitre précédent nous a permis de dessiner les grands équilibres macro-économiques de la région, elle atteint ses limites lorsqu'il s'agit de définir des

politiques de terrain. Un département est rarement un territoire homogène ; il est une mosaïque d'espaces aux profils et aux dynamiques variés. Pour une action publique efficace et ciblée, il est donc nécessaire d'adopter une grille de lecture plus fine, alignée sur les territoires de projet que sont les Établissements Publics de Coopération Intercommunale (EPCI).

Cette partie de notre étude a pour objectif de dépasser la vision administrative traditionnelle pour révéler une nouvelle géographie, fonctionnelle et opérationnelle, de l'économie régionale. En regroupant les EPCI qui partagent des caractéristiques similaires, nous cherchons à identifier un nombre restreint de "familles" de territoires, pour lesquelles des stratégies de développement sur-mesure pourront être conçues.

a. Méthodologie du Clustering de Profils

Pour identifier ces typologies de territoires, nous avons mis en œuvre une analyse par clustering (ou "classification non supervisée"), une méthode issue du Machine Learning. L'objectif n'est plus de comparer les territoires sur un seul indicateur, mais de les regrouper en fonction de la similarité de leur structure économique globale.

La démarche a été menée en deux temps :

b. Création de l'ADN Économique de chaque EPCI

La première étape a consisté à construire une "carte d'identité" ou un "ADN" sectoriel pour chaque intercommunalité de la région. Pour ce faire, nous avons utilisé les données détaillées du fichier Sirene pour calculer, pour chaque EPCI, la **part relative de chaque grand secteur d'activité** dans son nombre total d'établissements (Voir tableau annexes).

Par exemple, le profil d'un EPCI "A" pouvait être [Industrie : 40%, Commerce : 25%, Construction : 15%, Services : 20%], tandis que celui d'un EPCI "B" était [Industrie : 10%, Commerce : 30%, Construction : 10%, Services : 50%]. Cette méthode permet de caractériser la spécialisation de chaque territoire indépendamment de sa taille, en se concentrant sur sa structure intrinsèque.

c. Regroupement par l'Algorithme K-Means (avec k=4)

Une fois cet "ADN" calculé pour tous les EPCI, nous avons appliqué l'algorithme **K-Means**. Le rôle de cet algorithme est de partitionner l'ensemble des EPCI en un nombre de groupes (clusters) défini à l'avance, en minimisant la distance entre les membres d'un même groupe et en la maximisant entre les groupes. En d'autres termes, il crée des familles de territoires qui se ressemblent le plus possible entre eux et qui sont les plus différents possibles des autres familles.

Le choix de créer **4 clusters (k=4)** n'est pas arbitraire. Il est le résultat d'une analyse statistique préalable (la "méthode du coude", présentée en annexe) qui a identifié 4 comme étant un nombre optimal de typologies pour décrire la diversité des profils d'EPCI de la région, offrant le meilleur compromis entre finesse d'analyse et lisibilité stratégique.

Cette démarche rigoureuse nous a ainsi permis d'identifier quatre grandes familles de territoires en Région Centre-Val de Loire, dont la carte et les profils détaillés sont présentés dans les sections suivantes.

4. Cartographie des 4 Familles de Territoires

La méthodologie de clustering décrite précédemment nous a permis de classer chaque Établissement Public de Coopération Intercommunale (EPCI) de la région dans l'un des quatre profils économiques que nous avons identifiés. Le résultat de cette classification est plus parlant lorsqu'il est représenté visuellement.

La carte ci-dessous est la visualisation centrale de notre analyse. Elle représente l'ensemble des EPCI de la Région Centre-Val de Loire, où chaque territoire est coloré en fonction de la famille (ou "cluster") à laquelle il a été assigné par l'algorithme.

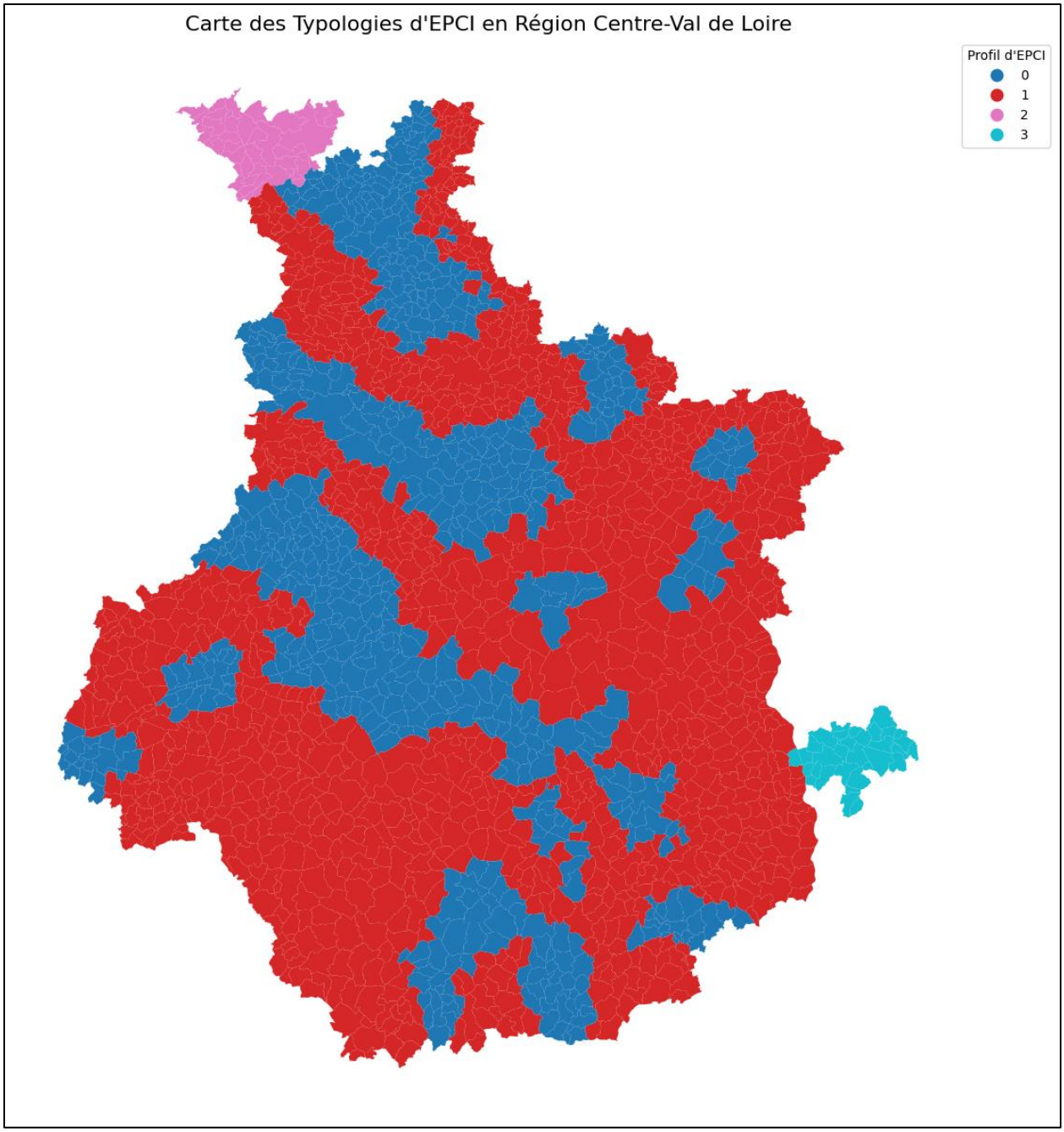

Source : Analyse de l'auteur

Cette carte dessine une nouvelle géographie économique de la région, une géographie "fonctionnelle" qui ne se superpose pas nécessairement aux frontières administratives traditionnelles des départements. Elle met en évidence des ensembles de territoires qui, bien que parfois non contigus, partagent un ADN économique commun et font donc face à des enjeux et des défis similaires.

L'observation de cette carte permet d'ores et déjà d'identifier visuellement la structuration de l'espace régional : on y distingue les grands pôles métropolitains, les vastes territoires industriels, ainsi que les zones dont l'économie est plus présentielle ou rurale. La description détaillée de la composition et des caractéristiques de chaque famille de territoires, identifiée ici par une couleur, fera l'objet de la section suivante.

5. Description Détaillée des 4 Profils d'EPCI

L'application de l'algorithme de clustering a permis de classifier les EPCI de la région en quatre profils distincts basés sur leur "ADN" sectoriel. L'analyse détaillée de ces groupes révèle que deux d'entre eux (clusters 1 et 3) correspondent à des intercommunalités uniques situées hors du périmètre strict de la région et peuvent être considérés comme des artefacts statistiques. L'analyse se concentrera donc sur les deux clusters massifs qui structurent véritablement l'économie régionale.

a. Profil A : Le Socle de l'Économie Présentielle et Rurale (Cluster 0)

C'est le profil le plus répandu, constituant le tissu économique de base de la majorité du territoire régional. Regroupant **55 EPCI,** il est le groupe est le plus large et est composé principalement des communautés de communes couvrant les zones rurales et les petites villes. On y retrouve par exemple la *CC Cœur de Beauce*, la *CC Loches Sud Touraine*, la *CC Sauldre et Sologne* ou encore la *CC du Grand Chambord*.

Son ADN économique est celui de la proximité. Il n'est pas dominé par un seul secteur, mais par un équilibre de quatre piliers essentiels à la vie locale :

- **Autres services marchands hors intérim :** 27.0%
- **Services non-marchands** (services publics, associations...) : 22.4%
- **Commerce :** 15.9%
- **Construction :** 15.6%. L'Industrie (11.0%) y est présente mais en retrait, n'étant pas le principal moteur de ces territoires.

Ce cluster représente la **fondation de l'économie locale et résidentielle**. Sa fonction première est de servir les habitants et les entreprises du territoire. Il est composé majoritairement de TPE, d'artisans, de commerçants et de professions libérales.

Bien que son poids dans les grands indicateurs économiques régionaux soit diffus, il est **essentiel au maillage territorial, à la cohésion sociale et à la qualité de vie**. Les enjeux pour ces 55 EPCI sont le maintien des services, l'accompagnement des TPE dans leurs transitions (numérique, écologique) et la facilitation de la transmission d'entreprise.

b. Profil B : Les Pôles Urbains, Commerciaux et de Services (Cluster 2)

Ce second profil regroupe tous les grands centres de décision, d'emploi et de consommation de la région. Il est composé de **25 EPCI**, incluant systématiquement les **deux métropoles** (*Orléans Métropole*, *Tours Métropole Val de Loire*) et les **principales agglomérations** (*Bourges Plus*, *Chartres Métropole*, *Châteauroux Métropole*, *Agglo du Pays de Dreux*, *Agglopolys (Blois)*, etc.).

L'ADN de ce cluster est clairement orienté vers une économie diversifiée, urbaine et d'échanges :

- **Autres services marchands hors intérim :** 28.2%
- **Commerce :** 20.8%
- **Services non-marchands :** 19.8% *Notons que la part du Commerce est significativement plus élevée que dans le profil A, et celle de la Construction plus faible.*

Ce cluster représente les **moteurs économiques et les cœurs battants** de la région. C'est ici que se concentrent les emplois à plus forte valeur ajoutée, les sièges sociaux, les grandes infrastructures commerciales, l'enseignement supérieur et la recherche.

Leur dynamisme et leur attractivité sont vitaux pour l'ensemble de la région. Les stratégies pour ces territoires doivent viser à **renforcer leur compétitivité** en tant que pôles de services supérieurs, à gérer la pression foncière, et à assurer une bonne connexion avec leurs arrière-pays (les territoires du profil A).

c. Profil C : Le Cas Spécifique de "l'Interco Normandie Sud Eure" (Cluster 1)

L'analyse fait émerger un troisième cluster qui ne contient qu'**un seul EPCI**. Il s'agit d'un profil très atypique qui a été isolé par l'algorithme en raison de sa composition sectorielle unique.

Ce territoire composé de la **Communauté de communes Interco Normandie Sud Eure** présente une hyper-spécialisation dans les services, avec une absence totale d'établissements employeurs dans les secteurs de l'Industrie, la Construction, le Commerce ou l'Hôtellerie-restauration dans les données traitées.

- **Services non-marchands :** 66.7%
- **Autres services marchands hors intérim :** 33.3%

La présence de ce cluster est un **artefact statistique** dû au périmètre des données initiales. La "CC Interco Normandie Sud Eure" est un territoire de la Région Normandie, limitrophe de l'Eure-et-Loir. Son profil économique, très différent de celui des EPCI du Centre-Val de Loire, a logiquement conduit l'algorithme à le placer dans une catégorie à part.

Ce cluster ne représente donc pas une typologie de territoire pertinente pour la stratégie de la Région Centre-Val de Loire et est présenté ici par souci d'exhaustivité méthodologique.

d. Profil D : Le Cas Spécifique de "Les Bertranges" (Cluster 3)

De manière similaire au profil précédent, ce quatrième et dernier cluster est également composé d'un unique EPCI que l'algorithme a isolé en raison de sa structure très particulière.

L'ADN de ce territoire (la **Communauté de communes Les Bertranges**) est marqué par une forte présence de l'hôtellerie-restauration et des services non marchands, et une absence totale d'autres types de services marchands.

- **Hôtellerie-restauration :** 33.3%
- **Services non-marchands :** 33.3%
- **Commerce :** 16.7%
- **Construction :** 16.7%

Tout comme le Cluster 1, il s'agit d'un **artefact statistique**. La "CC Les Bertranges" est un territoire de la Région Bourgogne-Franche-Comté, limitrophe du département du Cher.

Son profil économique, potentiellement orienté vers le tourisme ou des services publics spécifiques, est suffisamment unique pour que l'algorithme ne puisse le rattacher à aucune des deux grandes familles de territoires du Centre-Val de Loire. Il est donc également **exclu du champ de l'analyse stratégique** et des préconisations qui suivront.

La mise en évidence de ces deux cas spécifiques confirme la robustesse de l'analyse, qui a su isoler les exceptions et identifier les deux grands profils structurels (les Pôles Urbains et le Socle Rural) sur lesquels doit se baser la stratégie régionale.

V. PRECONISATIONS : POUR DES STRATEGIES TERRITORIALISEES

L'analyse menée dans ce rapport a révélé que la Région Centre-Val de Loire n'est pas un bloc économique homogène, mais une mosaïque de territoires aux profils et aux dynamiques bien distincts. La principale conclusion de notre analyse par clustering est la nécessité d'abandonner une approche "taille unique" pour adopter des stratégies de développement sur-mesure, adaptées à l'ADN économique de chaque grande famille de territoires.

Les recommandations qui suivent sont donc structurées non pas par département, mais selon les deux grandes typologies d'EPCI que nous avons identifiées : le "Socle Rural et de Proximité" et les "Pôles Urbains et de Services". Chaque recommandation vise à répondre aux enjeux spécifiques de ces écosystèmes pour maximiser l'impact des investissements publics.

1. Plan d'Action pour le Profil A : Animer le "Socle Rural et de Proximité"

Ce profil, qui regroupe 55 EPCI, constitue le maillage vital de la région. Sa stratégie doit viser à **maintenir, animer et accompagner la transformation** de son tissu économique composé majoritairement de TPE.

- **Préconisation 1 : Lancer un "Pacte Régional pour l'Économie de Proximité".** Créer un programme de soutien spécifiquement dédié aux TPE de ces territoires, axé sur trois volets :
  - **Transition Numérique :** Une aide directe (chèque numérique) pour financer la création d'un site web, la mise en place d'un système de vente en ligne ou l'amélioration de la visibilité sur internet.
  - **Transition Écologique :** Une subvention pour les investissements des artisans et commerçants visant à améliorer leur performance énergétique (isolation des locaux, changement d'équipements).
  - **Facilitation de la Transmission :** Créer une plateforme régionale en ligne, en partenariat avec les Chambres de Métiers et de l'Artisanat et les Chambres de Commerce et

d'Industrie, pour mettre en relation les dirigeants partant à la retraite et de potentiels repreneurs, avec un bonus régional pour les reprises effectives en zone rurale.

- **Préconisation 2 : Soutenir les "Cœurs de Bourgs".** Abonder un fonds régional de revitalisation pour cofinancer les projets portés par les communes et intercommunalités visant à renforcer l'attractivité des centres-bourgs : réhabilitation de locaux commerciaux vacants, création de halles de marché couvertes, ou mise en place de "conciergeries" de territoire regroupant plusieurs services (point postal, espace de coworking, dépôt de produits locaux).

2. Plan d'Action pour le Profil B : Renforcer les "Pôles Urbains et de Services"

Ce profil, qui regroupe les 25 principales agglomérations, est le moteur économique de la région. La stratégie doit viser à **renforcer sa compétitivité et son attractivité** pour les entreprises à forte valeur ajoutée et les talents.

- **Préconisation 1 : Créer des "Campus d'Excellence" Thématiques.** Renforcer les synergies entre les universités (Orléans, Tours) et les filières économiques clés de ces pôles. Co-financer des chaires de recherche-action et des projets de R&D collaboratifs entre PME, grands groupes et laboratoires publics sur des thématiques phares comme la cosmétique, la pharmacie, la logistique durable ou les services numériques.
- **Préconisation 2 : Lancer une "Offensive Talents".** Mettre en place une politique agressive de marketing territorial ciblée sur les profils qualifiés (ingénieurs, développeurs, chercheurs) en Île-de-France et dans les autres grandes métropoles, en vantant la qualité de vie et les opportunités de carrière au sein des pôles régionaux. Cette campagne pourrait être couplée à une aide à l'installation pour les nouveaux arrivants dans des secteurs jugés prioritaires.
- **Préconisation 3 : Investir dans les Infrastructures d'Attractivité.** Flécher des investissements régionaux vers les projets d'infrastructures qui améliorent le cadre de vie métropolitain : développement des réseaux de transports en commun décarbonés (tramway, bus à haut niveau de service), soutien à la création de lieux culturels et événementiels, et facilitation des programmes de logement neuf de haute qualité environnementale.

VI. LIMITES DE L'ETUDE

Il convient de souligner que cette étude, malgré sa rigueur, comporte un certain nombre de limites inhérentes à son périmètre et à la nature des données mobilisées. Reconnaître ces limites est un gage de transparence et permet d'orienter les travaux futurs.

- **Une vision statique :** L'analyse présentée ici est une "photographie" de l'économie régionale à un instant T. Elle décrit les structures existantes mais ne capture pas les **dynamiques temporelles**. Elle ne nous renseigne pas sur les trajectoires de croissance ou de déclin des secteurs, ni sur les taux de création et de défaillance d'entreprises, qui sont pourtant des indicateurs essentiels de la vitalité économique.
- **Un périmètre d'analyse délimité :** Deux choix méthodologiques importants ont défini notre champ d'investigation. Premièrement, l'**exclusion du secteur agricole primaire**, bien que justifiée pour se concentrer sur l'économie marchande et de services, laisse de côté un pan majeur de l'économie et de l'identité des territoires ruraux. Deuxièmement, le choix de se focaliser sur les **établissements employeurs** pour correspondre aux données URSSAF signifie que le poids du travail indépendant et des auto-entrepreneurs, en forte croissance, est sous-estimé dans notre décompte des acteurs économiques.
- **Une approche essentiellement quantitative :** Notre méthodologie, basée sur des données statistiques, révèle le "quoi" et le "où" mais ne peut pas toujours expliquer le "pourquoi" en profondeur. Elle identifie des spécialisations mais ne peut, à elle seule, en expliquer les causes historiques, culturelles ou entrepreneuriales. L'analyse gagnerait donc à être complétée par une démarche qualitative.

VII. Gouvernance et Évolution : Vers un Observatoire Dynamique des Territoires

L'analyse présentée dans ce rapport offre une "photographie" de l'économie régionale à un instant T. Pour transformer cet outil de connaissance en un véritable instrument de pilotage stratégique sur le long terme, il est impératif de mettre en place une gouvernance claire et une stratégie de mise à jour. Nous préconisons donc de pérenniser ce modèle en le faisant évoluer vers un observatoire dynamique des profils économiques territoriaux.

Ce processus de gouvernance reposerait sur trois piliers fondamentaux :

1. Instaurer un Cycle de Mise à Jour Annuel

Pour que le modèle reste pertinent, il doit être actualisé régulièrement.

- **Fréquence :** Nous recommandons une mise à jour complète sur une base **annuelle**. Ce rythme permet de capter les évolutions structurelles sans être pollué par les fluctuations conjoncturelles à très court terme.
- **Processus :** Chaque année, au deuxième trimestre, les données sources seraient renouvelées :

- Intégration des données **URSSAF** consolidées de l'année N-1 pour les effectifs et la masse salariale.
- Mise à jour de la base des établissements à partir du dernier millésime disponible de **Sirene (INSEE)**.

Ceci permettra de disposer chaque année d'un portrait actualisé permettant de mesurer les trajectoires d'évolution.

2. Mettre en Place un Processus de Validation et de Recalibrage du Modèle

La mise à jour ne doit pas être un simple rafraîchissement des données. C'est l'occasion de revalider le modèle de classification lui-même.

- **Recalibrage de l'algorithme :** Après chaque mise à jour des données, l'algorithme **K-Means** doit être relancé sur les nouveaux profils d'EPCI.
- **Validation du nombre de clusters :** La "méthode du coude" sera de nouveau appliquée pour vérifier si le nombre optimal de 4 clusters reste pertinent ou si de nouvelles familles de territoires émergent.
- **Analyse des trajectoires :** L'enjeu principal sera d'analyser les changements de profils. Si un EPCI passe du cluster A ("Socle Rural") au cluster B ("Pôle Urbain"), c'est un signal fort de dynamisme qui doit alerter les services de la Région et faire l'objet d'une analyse approfondie.

3. Instituer une Veille Stratégique et Qualitative

Comme souligné dans les limites, l'approche quantitative révèle le "quoi" mais pas toujours le "pourquoi".

- **Veille sur les données :** Mettre en place une veille sur les nouvelles sources de données qui pourraient enrichir le modèle (ex: données sur la création/défaillance d'entreprises, données sur les filières touristiques, données sur l'immobilier d'entreprise).
- **Enquêtes qualitatives :** Pour expliquer les évolutions observées, des entretiens qualitatifs ciblés devront être menés auprès des acteurs de terrain (agents de développement économique des EPCI, chambres consulaires, etc.) dans les territoires connaissant les mutations les plus rapides. Cela permettra de contextualiser les chiffres et d'affiner les préconisations.

En adoptant cette stratégie de gouvernance, la Région Centre-Val de Loire ne se dote pas seulement d'une étude ponctuelle, mais d'un **baromètre permanent**, capable de détecter les dynamiques territoriales, d'objectiver les décisions et d'adapter ses politiques de développement en continu.

VIII. CONCLUSION GENERALE

Au terme de cette analyse, une vision renouvelée et à double focale de l'économie du Centre-Val de Loire émerge. La démarche a permis de dépasser les lectures traditionnelles pour offrir une perspective à la fois macro-territoriale et opérationnelle.

L'analyse comparative des départements a d'abord mis en lumière une hiérarchie économique claire, soulignant les poids respectifs et les grandes spécialisations de chaque territoire. Cependant, l'analyse plus fine par clustering a révélé une géographie économique fonctionnelle, structurée non pas par les frontières administratives, mais par des typologies d'EPCI partageant un ADN économique commun.

Nous avons ainsi pu distinguer clairement les grands pôles urbains et de services des territoires constituant le socle rural et de proximité.

L'enseignement principal de ce travail est donc la **nécessité impérieuse d'adapter et de différencier les politiques publiques**. La grande hétérogénéité des profils de territoires démontre qu'une stratégie régionale unique serait inefficace. La pertinence de l'action publique et l'optimisation des investissements dépendront de la capacité de la Région à déployer des outils sur-mesure : un accompagnement de proximité pour le vaste tissu de TPE qui maille les zones rurales, et un soutien à l'excellence et à l'attractivité pour les métropoles et les pôles secondaires qui sont les moteurs de la région.

IX. ANNEXES

Annexe A : Déclaration sur l'Éthique et la Conformité au RGPD

1. Finalité du Traitement et Nature des Données

La présente étude a été menée pour le compte de l'Observatoire Économique de la Région Centre-Val de Loire dans une mission d'intérêt public visant à analyser les dynamiques économiques territoriales pour orienter les politiques de développement.

Les sources de données mobilisées sont les suivantes :

- **La base de données Sirene de l'INSEE :** Contient des informations sur les entreprises (personnes morales) et les établissements. Bien que le nom d'un entrepreneur individuel puisse y figurer, notre analyse s'est portée sur les données structurelles (localisation, secteur d'activité, SIRET) et n'a jamais traité ces informations à des fins d'analyse sur des personnes physiques.
- **Les données agrégées de l'URSSAF :** Contiennent des données statistiques sur l'emploi et la masse salariale, agrégées au niveau du département et du secteur. Ces données sont, par nature, anonymisées et ne permettent pas d'identifier des individus.
- **Les référentiels géographiques (INSEE, IGN) :** Contiennent des informations sur des entités géographiques (communes, EPCI) et non sur des personnes.

2. Principes de Traitement et Méthodes d'Anonymisation

Conformément aux principes du RGPD, une approche de minimisation des données a été appliquée.

- **Anonymisation par Agrégation :** L'ensemble des analyses présentées dans ce rapport (tableaux de bord, typologies) repose sur des données agrégées. Les informations individuelles des établissements ont été utilisées pour calculer des totaux (nombre

d'établissements, etc.) ou des profils moyens à des échelles géographiques (EPCI, département), ce qui constitue une méthode d'anonymisation robuste.

- **Pseudo-anonymisation :** Dans le cadre de l'analyse de clustering, chaque établissement a été traité comme un point de donnée technique (coordonnées, secteur, taille) sans utiliser d'informations potentiellement identifiantes sur des personnes physiques.

3. Justification des Choix au Regard du RGPD

Le traitement de ces données est justifié par sa nécessité pour la réalisation de la mission d'intérêt public confiée à l'Observatoire. L'objectif n'est pas d'analyser des individus, mais de comprendre des dynamiques économiques collectives pour permettre une allocation plus juste et plus efficace des ressources publiques, au bénéfice du développement économique de l'ensemble du territoire régional. Toutes les sources de données utilisées sont publiques ou semi-publiques et ont été traitées dans le respect de leurs conditions d'utilisation.

Annexe 1 : secteur le plus faible économiquement par département.

	Departement	Secteur_Plus_Faible_Eco
17	Indre	Hôtellerie-restauration
5	Cher	Intérim
10	Eure-et-Loir	Hôtellerie-restauration
31	Loir-et-Cher	Hôtellerie-restauration
26	Indre-et-Loire	Intérim
38	Loiret	Hôtellerie-restauration

Annexe 2 : Secteur le moins dense par département

	Departement	Secteur_Moins_Dense
19	Indre	Intérim
5	Cher	Intérim
33	Loir-et-Cher	Intérim
12	Eure-et-Loir	Intérim
26	Indre-et-Loire	Intérim
40	Loiret	Intérim

Annexe 3 : Secteur dominant par département

	Departement	Secteur_Dominant
35	Loiret	Autres services marchands hors intérim
21	Indre-et-Loire	Autres services marchands hors intérim
11	Eure-et-Loir	Industrie
32	Loir-et-Cher	Industrie
4	Cher	Industrie
18	Indre	Industrie

Annexe 4 : Les principaux indicateur par département

	Departement	Nombre_Etablissements	Effectifs	Masse_Salariale	Salaire_Moyen_Mensuel	Taille_Moyenne_Etablissement
0	Cher	7966	66003	514498509	2598.0	8.3
1	Eure-et-Loir	11976	101092	790690946	2607.0	8.4
2	Indre	6334	49040	360222280	2448.0	7.7
3	Indre-et-Loire	18231	174888	1391459440	2652.0	9.6
4	Loir-et-Cher	9815	80649	613224084	2535.0	8.2
5	Loiret	19149	195800	1591947770	2710.0	10.2
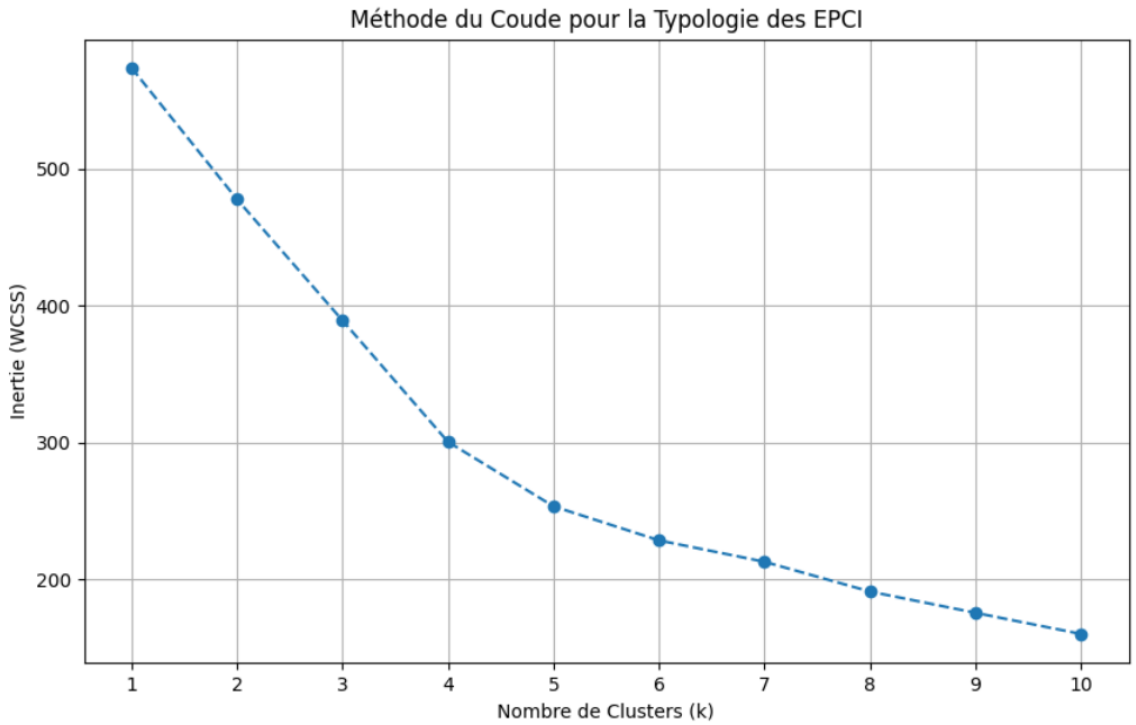
Annexe 5 : Méthode du coude pour déterminer le nombre de clusters